ABC 3G
09:34 AM
Kaart
Lijst
Opties
Informatie over de brug of aanlegplaats
Zoeken...

ABC 3G
09:34 AM
Kaart
Lijst
Opties
Filter
Bergumerdam
Hoogte, breedte
2,3km
Vrouwenpoortbrug
Hoogte, breedte
3,5km
Heechhout
Hoogte, breedte
4,3km
Potmargebrug
Hoogte, breedte
22,3km

ABC 3G
09:34 AM
Brug-/aanlegplaatsnaam
Terug
Informatie over de brug/aanlegplaats
Ga naar
Plan route

ABC 3G
09:34 AM
Kaart
Lijst
Opties
Bootgegevens:
Hoogte
Breedte
Kaarttype:
Map
satteliet
Hybride
Over deze App

Huidige positie aanlegplaatsen

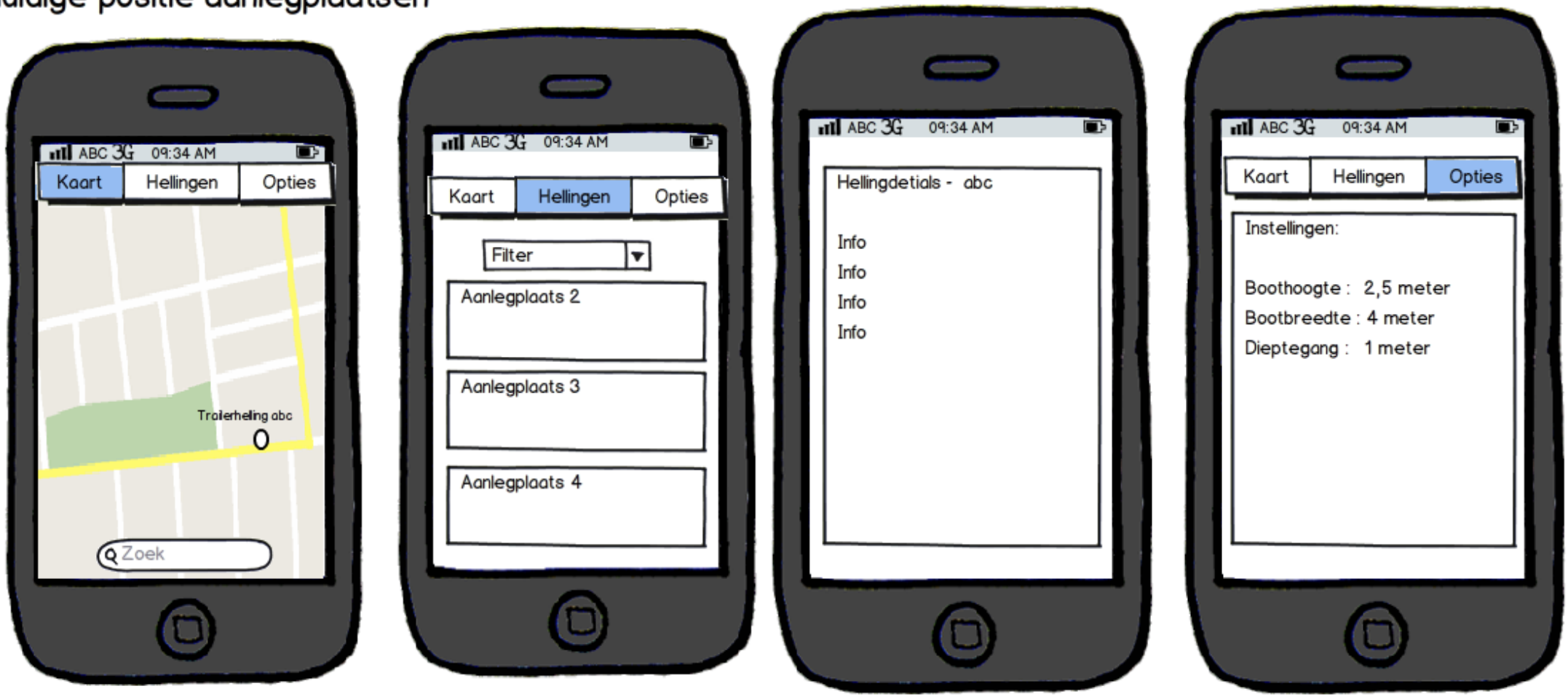

Huidige positie Leeuwarden

ABC 3G
09:34 AM
Zoeken...
Informatie over de brug of aanlegplaats
Kaart
Lijst
Opties

ABC 3G
09:34 AM
Filter
Bergumerdam
Hoogte, breedte
2,3km
Vrouwenpoortbrug
Hoogte, breedte
3,5km
Heechhout
Hoogte, breedte
4,3km
Potmargebrug
Hoogte, breedte
22,3km
Kaart
Lijst
Opties

ABC 3G
09:34 AM
Brug-/aanlegplaatsnaam
Terug
Informatie over de brug/aanlegplaats
Ga naar
Plan route

ABC 3G
09:34 AM
Bootgegevens:
Hoogte
Breedte
Kaarttype:
Map
satteliet
Hybride
Over deze App
Kaart
Lijst
Opties

Huidige positie aanlegplaatsen

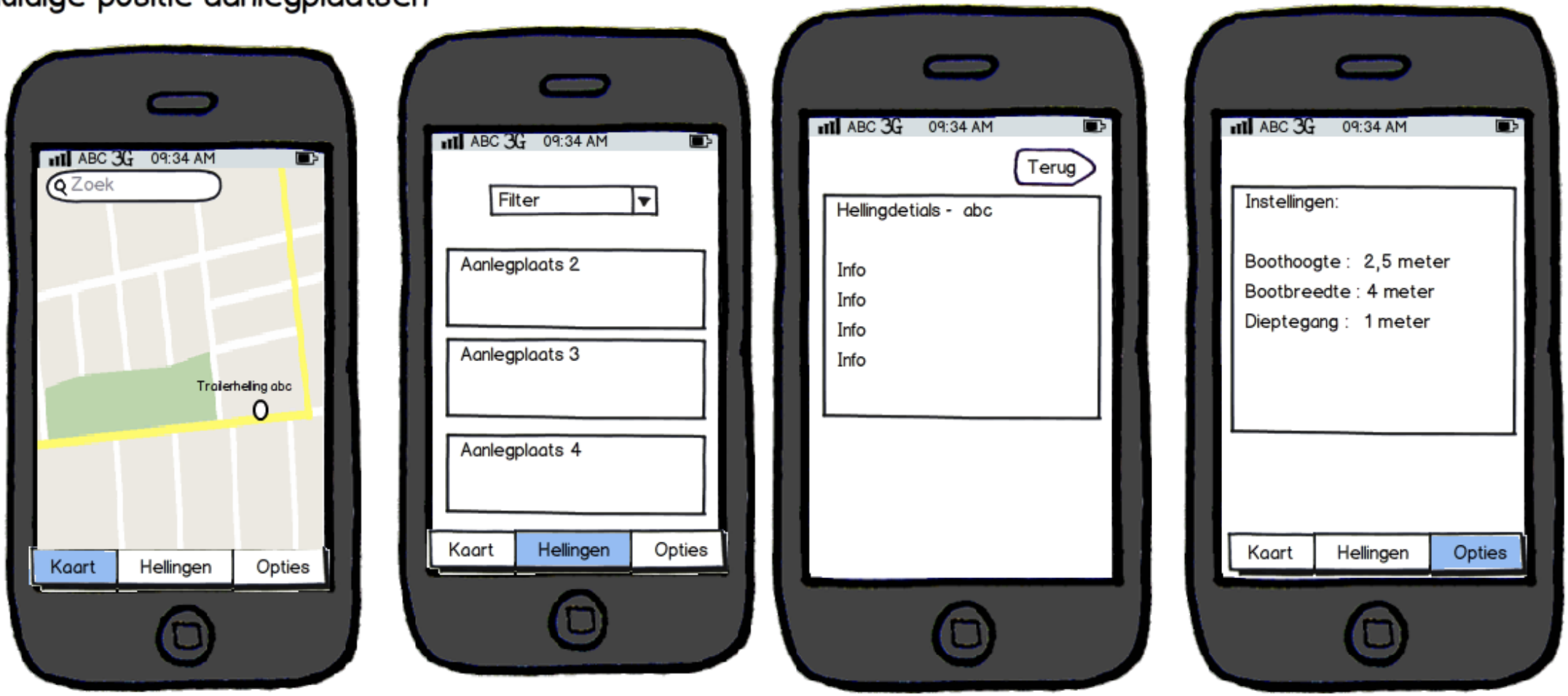

Huidige positie Leeuwarden